תכנית מס' 603-0271296

מאושרת

מתחם אבן עזרא, אשדוד

תשריט- מצב מאושר

איחוד וחלוקה	סמכות ראשית	אופי התכנית
ללא הסכמת בעלים	ועדה מחוזית	תכנית שניתן מכוחה להוציא היתרים

מחוז : דרום

מרחב תכנון מקומי : אשדוד

רשות מקומית : אשדוד

ישוב: אשדוד

שטח התכנית : כ-20.1 דונם

קנה מידה: 1 : 500

אישור תכנית
פורסמה בילקוט פרסומים
מיום 3630

גושים וחלקות בתכנית:

גוש	סוג הגוש	חלקות בשלמותן	חלקי חלקות
2071	מוסדר	46-51,59,61,62,64,69,70	63,231,298,299
יחתימת מודד			

שלב: הגשה **מהדורה :** 07 **תאריך :** 13.01.2016

חותמות מוסד התכנון :

שמות וחתימות :

מגיש התכנית	שם: מרגנית אחזקות בע"מ		תאריך חתימה:
	כתובת: האורגים 29, אשדוד		
	מקום: 08-8533595	פקס: 08-8561062	דוא"ל: teddy@bezeqint.net
היזם בפועל	שם: מרגנית אחזקות בע"מ		תאריך חתימה:
	כתובת: האורגים 29, אשדוד		
	מקום: 08-8533595	פקס: 08-8561062	דוא"ל: teddy@bezeqint.net
עורך התכנית	שם: צפר גרשון-צפר ברק אדריכלים ומתכנני ערים בע"מ		תאריך חתימה:
	כתובת: מרכז בעלי מלאכה 40 תל אביב		
	מקום: 03-5189426	פקס: 03-5184295	דוא"ל: mail@zippor.co.il
מודד	שם: סמי מרקס שרותי מדידות		תאריך חתימה:
	כתובת: אחלמה 32, אשדוד		
	מקום: 08-8671777	פקס: 08-8541366	דוא"ל: Samir2@012.net.il

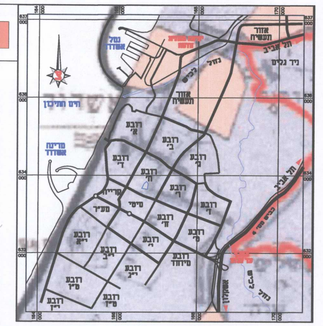
הנני מצהיר בזאת כי מדידת המפה הטופוגראפית/המצבית המהווה רקע לתכנית זו, נערכה על ידי ביום: _____ והיא הוכנה לפי הוראות נוהל מבאית ובהתאם להוראות החוק ולתקנות המודדים שבתוקף. דיוק הקו הכחול והקדסטר: מדידה גרפית/קו כחול(גבול) ברמה אנליטית/ מדידה אנליטית מלאה ברמת תצ"ר (כולל הקו הכחול)

שם המודד: ל'יאניב ברנובי'ץ מספר רישיון: 1329 חותמת: _____ תאריך: _____

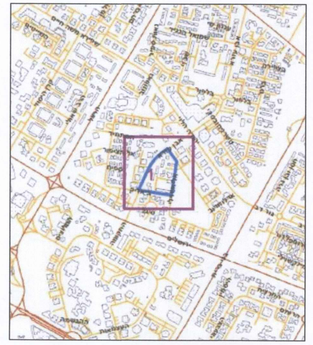
P:\N1725\Taba\Tasrit\ Tasrit Even Ezra Meushar 13.01.16.dwg Jan 13, 2016 - 2 : 51pm

אזורים רגישים להחדרת נגר עילי למי תהום

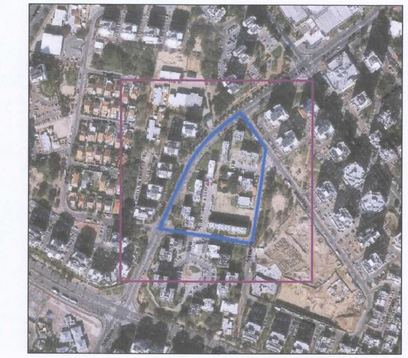
תרשים סביבה על רקע תמ"א 34\ב\4 1:50000



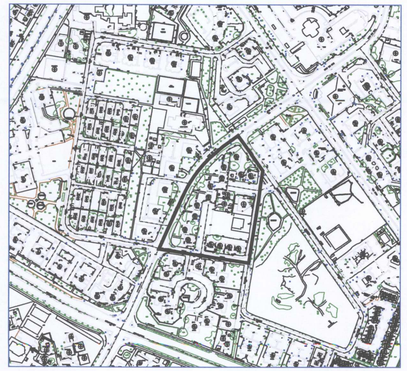
תרשים התמצאות 1:15000



תרשים סביבה 1:5000



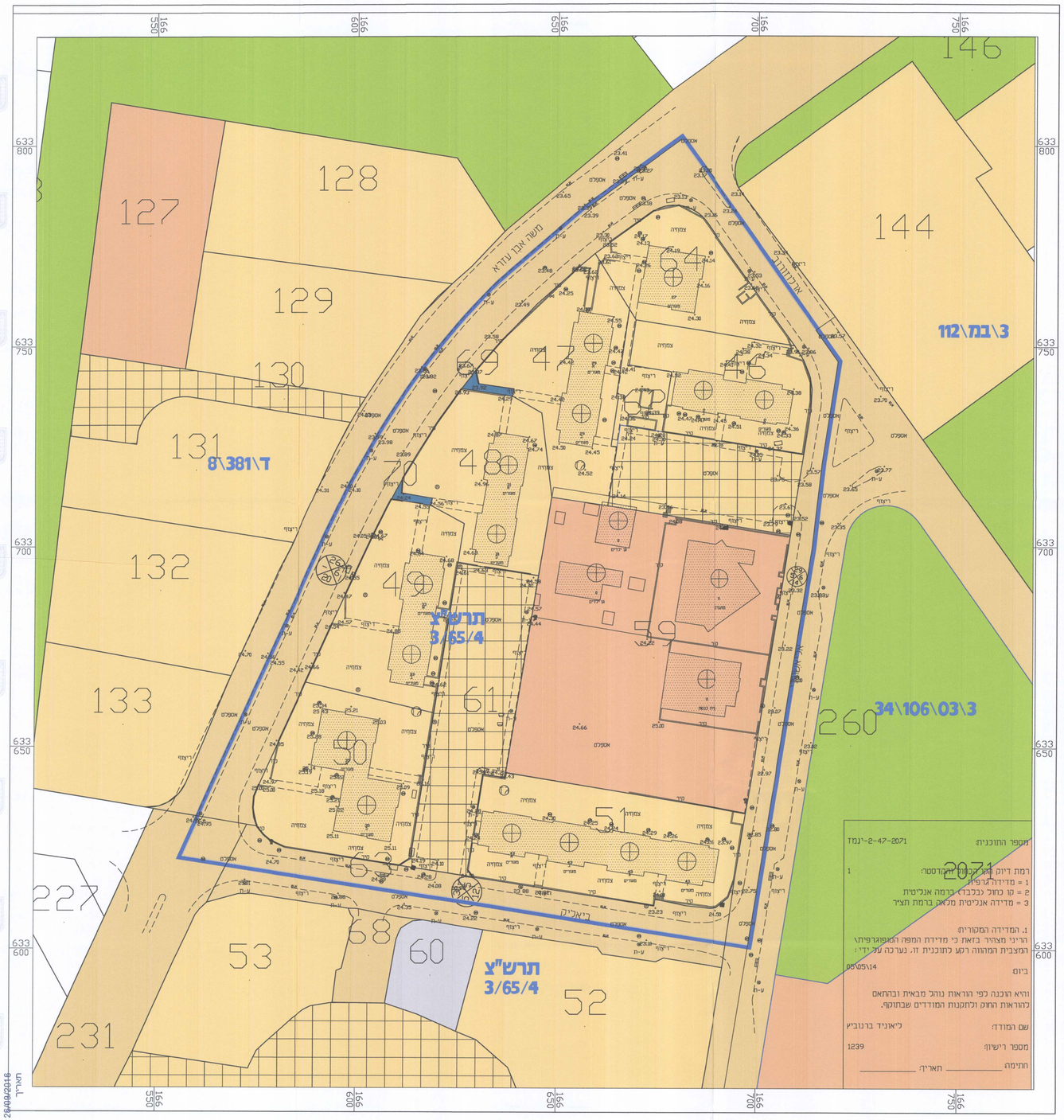
תרשים התמצאות 1:5000



מקרא מצב מאושר

- תוויה
- גבול תוכנית כתצוגה
- גבול תא שטח
- מגורים
- מבנים ומוסדות ציבור
- דרך מאושרת
- שטח ציבורי פתוח
- מסחר
- שביל
- רזרבה

מספר הדרך
אורך בקנ"מ
רוחב הדרך



חתימת המנהל, החשב"ה - 1965
תאריך הגשת התכנית - טרם דרים :
תאריך ועדת המחוזית/עליה בים :
תאריך אישור התכנית
תאריך ההודעה בעיתון
20/09/2016

תכנית מס' 603-0271296

מתחם אבן עזרא, אשדוד

תשריט- מצב מאושר

איחוד וחלוקה	סמכות ראשית	אופי התכנית
ללא הסכמת בעלים	ועדה מחוזית	תכנית שניתן מכוחה להוציא היתרים

מחוז : דרום

מרחב תכנון מקומי : אשדוד

רשות מקומית : אשדוד

ישוב: אשדוד

שטח התכנית : כ-20.1 דונם

קנה מידה: 1:500 אורך תכנית

פורסמה בילקוט פרסומים מיום 7630 3814

גושים וחלקות בתכנית:

גוש	סוג הגוש	חלקות בשלמותן	חלקי חלקות
2071	מוסדר	46-51,59,61,62,64,69,70	63,231,298,299
חתימת מודד			

שלב: הגשה **מהדורה :** 07 **תאריך :** 13.01.2016

חותמות מוסד התכנון :

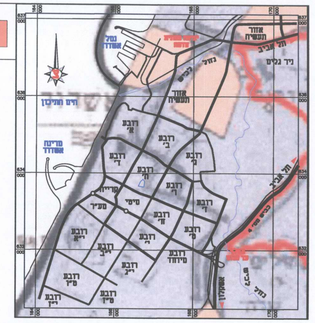
שמות וחתימות :

מגיש התכנית	שם: מרגנית אחזקות בע"מ			תאריך וחתימה :
	כתובת: האורגים 29, אשדוד			
	טלפון: 08-8533595	פקס: 08-8561062	דוא"ל: teddy@bezeqint.net	
היזם בפועל	שם: מרגנית אחזקות בע"מ			תאריך וחתימה :
	כתובת: האורגים 29, אשדוד			
	טלפון: 08-8533595	פקס: 08-8561062	דוא"ל: teddy@bezeqint.net	
עורך התכנית	שם: צפר גרשון-צפר ברק אדריכלים ומתכנני ערים בעמ			תאריך וחתימה :
	כתובת: מרכז בעלי מלאכה 40 תל אביב			
	טלפון: 03-5189426	פקס: 03-5184295	דוא"ל: mail@zippor.co.il	
מודד	שם: סמי מרקס שירותי מדידות			תאריך וחתימה :
	כתובת: אחלמה 32, אשדוד			
	טלפון: 08-8671777	פקס: 08-8541366	דוא"ל: Samim2@012.net.il	

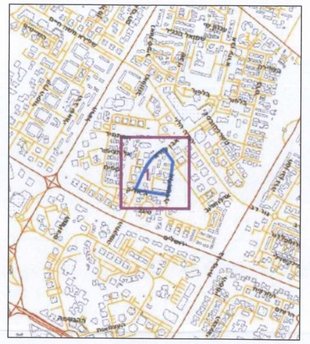
הנני מצהיר בזאת כי מדידת המפה הטופוגראפית/המצבית המהווה רקע לתכנית זו, נערכה על ידי ביום: _____ והיא הוכנה לפי הוראות נוהל מבאית ובהתאם להוראות החוק ולתקנות המודדים שבתוקף. דיוק הקו הכחול והקדסטר: מדידה גרפית/קו כחול(בלבד) ברמה אנליטית/ מדידה אנליטית מלאה ברמת תציר (כולל הקו הכחול)

שם המודד: ליאוניד ברנבייץ מספר רישיון: 1329 חתימה: _____ תאריך: _____

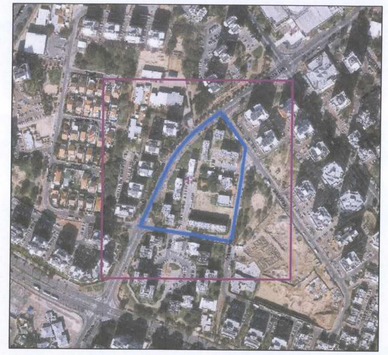
P:\N1725\Taba\Tasrit\ Tasrit Even Ezra Meushar 13.01.16.dwg Jan 13, 2016 - 2:51pm



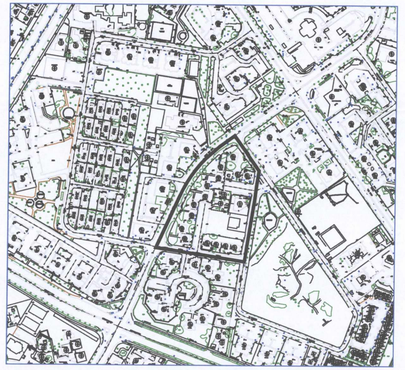
תרשים סביבה על רקע תמ"א 34\ב\4 1:50000



תרשים התמצאות 1:15000



תרשים סביבה 1:5000



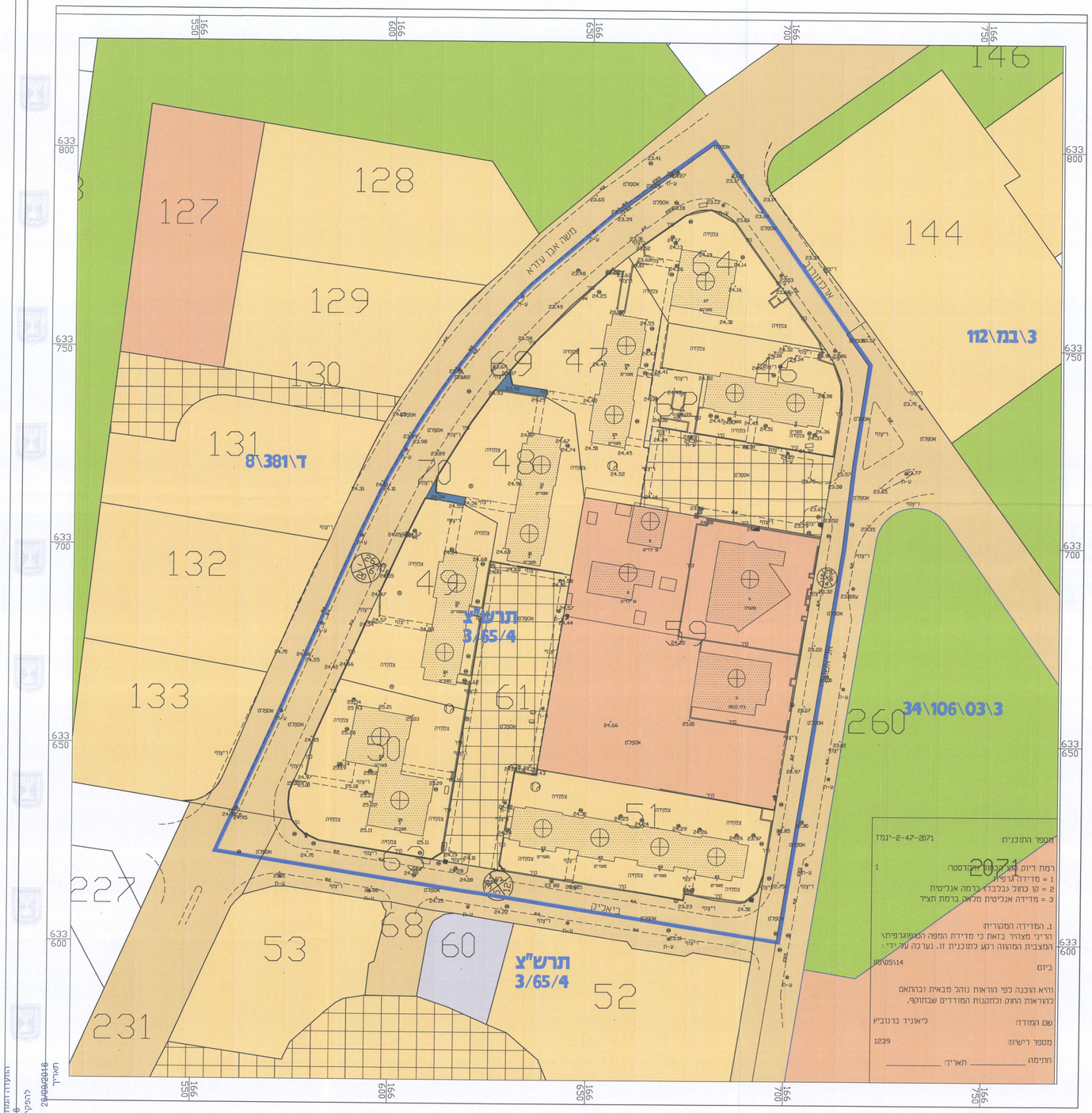
תרשים התמצאות 1:5000

אזורים רגישים להחזרת נגר עילי למי תהום

מקרא מצב מאושר

- תוויה
- גבול תוכנית לתצוגה
- גבול תא שטח
- מגורים
- מבנים ומוסדות ציבור
- דרך מאושרת
- שטח ציבורי פתוח
- מסחר
- שביל
- רדיוסה

מספר הדרך / שם הדרך / רוחב הדרך



מקור מידע	מדידה מצבית
תאריך	28/09/2016
מהדורה	07
מאת	ליאוניד ברנבייץ
מקנה מידה	1:500

תשריט התכנית והגבלת התחזית

להסיר את הסימון

משרד הפנים - מחוז דרום

מקור התכנון: תשריט, הוראות, נספחים 1965 -

חוק התכנון והבנייה, התשכ"ה - 1965

תכנית מפורטת

מס' 603-0271296

מתחם אבן עזרא, אשדוד

תשריט מצב מוצע	גיליון 1 מתוך 1		
מחוז	דרום		
מרחב תכנון מקומי	אשדוד		
רשות מקומית	אשדוד		
ישוב	אשדוד		
תכנית בסמכות	מחוזית		
איחוד וחלוקה	איחוד ו/או חלוקה ללא הסכמת כל הבעלים בכל תחום התכנית/בחלק מתחום התכנית		
היתרים או הרשאות	תכנית שמכוחה ניתן להוציא היתרים או הרשאות		
מונה תדפיס התשריט	12		
מועד הפקה	05/11/2017	08:56	
שטח התכנית	20.1 דונם	קנה מידה	1:500

אישורים

שמות*

מגיש התכנית	טדי מנשה תאגיד: מרכזית אחזקות בע"מ
מגיש התכנית	רשות מקומית תאגיד: עיריית אשדוד
עורך ראשי	ברק צפור תאגיד: צפור גרשון- צפור ברק אדריכלים ומתכנני ערים בע"מ
יזם	טדי מנשה תאגיד: מרכזית אחזקות בע"מ

בעלי ענין בקרקע*

בבעלות רשות מקומית	תאגיד: עיריית אשדוד
בעלים	תאגיד: הסוכנות היהודית לארץ ישראל (ע"י עמיגור ניהול נכסים

טבלת גושים וחלקות*

מספר גוש	חלק/ כל הגוש	מספרי חלקות בשלמותן	מספרי חלקות בחלקיותן
2071	חלק	46-51,59,61-62,64,69-70	63,231,298-299

* הרשימה המלאה מפורטת בהוראות התכנית / בהודעה שפורסמה בעיתונות וברשומות

הריני מצהיר בזאת כי המפה הטופוגרפית/המצבית המהווה רקע לתכנית זו, נערכה על ידי ביום 28/10/17 והיא הוכנה לפי הוראות נוהל מבא"ת ובהתאם להוראות החוק ולתקנות המודדים שבתוקף. דיוק הקו הכחול והקו סגול

מדידה גרפית

לאוניד ברנוביץ	1239		
שם המודד	מספר רשיון	חתימה	תאריך

נערכת מצורכת 12.2015

מקרא

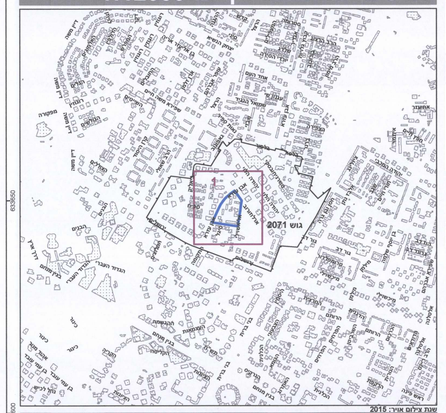
- מגורים ד
- מבנים ומוסדות ציבור
- דרך מאושרת
- דרך מוצעת
- זיקת -הנאה
- מבנה להריסה
- קו-בנין
- להריסה
- מידות

מקרא מפת מדידה

מקרא

- מבנה
- צריף/סככה/חממה
- אספלט
- אבן שפה
- דרך עפר
- גדר תיל \ רשת
- גדר אבן/קיר
- גדר אבן/ קיר אבן/ גדר/ בטון
- שפת ואדי
- מדרון עליון/ שיפוע סבעי
- עץ
- נקודת גובה אופיינית
- קו גובה משני (0.5, 1.0, 2.5 מ')
- קו גובה ראשי (5.0, 25, 10 מ')
- שוחת ביקורת כללית
- עמוד כללי
- ארון כללי
- עמוד תאורה
- עמוד תקשורת
- ע. חשמל עץ
- ע. חשמל בטון
- ע. חשמל חעלה
- ע.חשמל, זזית
- שוחת/ גוב מים
- שוחת ביוב
- שוחת ניקוז
- גוב תקשורת

תרשים התמצאות - קנ"מ 1:12000



תרשים סביבה - קנ"מ 1:3000



